Mtr. nr., ejerlav, sogn: 21 b
Øster Sundby, Aalborg købstads jorder.

Akt: Skab 8 *nr.* 122
(udfyldes af dommerkontoret)

Kreditors bopæl: Aalborg.

Gade og hus nr.:
Bakkegårdsvej 1.

Anmelder:
Aalborg Bys og Omegns Sparekasse.

Stempel kr. 20,-.

Pantebrev.

Underskrevne husejer SVEND AAGE MIKKELSEN, Aalborg,

erkender herved at være skyldig til **Aalborg Bys og Omegns Sparekasse** den sum kr. 10.000,-, hvilke ti tusinde kroner jeg forpligter mig----------
til at forrente fra udbetalingsdagen at regne med den rente, sparekassen til enhver tid måtte forlange for sine udlån mod pant i fast ejendom, for tiden --5¼-- % p. a., der betales med halvdelen hver **11. juni** og **11. december** termin, første gang 11. juni termin 1959 for det da forløbne tidsrum.
Denne kapital forpligter jeg mig til at forrente og afdrage i hver af de forannævnte terminer, første gang 11. juni termin 1959, for det da forløbne tidsrum med en halvårlig ydelse på for tiden kr. 340,- , hvoraf --5¼--% p. a. er renter af den til enhver tid skyldige restgæld, medens restbeløbet er afdrag, idet ydelsen dog forandres i samme forhold, som renten stiger eller falder.
Uanset disse afdragsbestemmelser kan kapitalen såvel af sparekassen som af debitor opsiges med 3 måneders varsel til indfrielse i en juni eller december termin.

Til sikkerhed for alle betalinger efter dette pantebrev gives herved sparekassen første prioritets panteret i den mig iflg. skøde tinglyst den 29/7 1955

tilhørende ejendom

matr. nr. 21 b Øster Sundby, Aalborg købstads jorder af hartkorn 0¼ alb.

DSS 88302261
76_E-A_122
Bulk Sort / Hvid
226829

Justitsministeriets genpartpapir. Til fortsættelse af dokumenter.

Bestillings-formular X
Jensen & Kjeldskov A/S, København.

Foranstående og jævnsides pantehæftelser: I n g e n.

Med hensyn til de ejendommen nu påhvilende servitutter og andre byrder bemærkes:

I n t e t.

Genpartens rigtighed bekræftes.
Civildommeren i Aalborg Købstad og Amt.

INDFØRT I DAGBOGEN
18. APR. 1959
AALBORG CIVILRET.

Lyst.

Løvrigt underkaster j e g m i g nedenstående trykte bestemmelser. (Justitsministeriets pantebrev-formular I.)

Jeg erklærer på tro og love, at jeg er ugift.

A a l b o r g, den 11. april 1959.

Svend Aage Mikkelsen.

Underskrevne bevidner herved, at ovenstående underskrift af debitor er ægte, at underskriftens dato er rigtig, og at debitor er myndig

Navn: I. Kristensen,	Navn: A. Bak,
stilling: Sparekasseassistent	stilling: Sparekassefuldmægtig
bopæl: Aalborg	bopæl: Aalborg

Mtr. nr., ejerlav, sogn: (i København kvarter) eller (i de sønderjydske landsdele) bd. og bl. i tingbogen, art. nr., ejerlav, sogn.

21 b Øster Sundby, Aalborg købstads jorder.

Stempel: kr. øre

Akt: Skab 16 nr. 122. (udfyldes af dommerkontoret)

Kø̸bers / Kreditors } bopæl: Aalborg

Gade og hus nr.:

Anmelder:

AALBORG BYS OG OMEGNS SPAREKASSE

fra Sr. Aa. Mikkelsen

RELAXATIONSPÅTEGNING

på pantebrev til AALBORG BYS OG OMEGNS SPAREKASSE, tinglyst 18. april 1959 for kr. 10.000,-.

18. MAJ 1961* 04864

-o-o-o-o-

Der meddeles tilladelse til, at matr. nr. 21 mn Øster Sundby, Aalborg købstads jorder, af areal: 64 m2 udgår af pantet.

AALBORG BYS OG OMEGNS SPAREKASSE, den 18/5-61

Steby A. Bak

Indført i dagbogen for Aalborg rets 3. afd.

den 18. MAJ. 1961

LYST

Linde

Genpartens rigtighed bekræftes.

DOMMEREN I AALBORG RET. 3. AFD.

Linde

Justitsministeriets genpartspapir. Til skøder, skadesløsbreve, kvitteringer til udslettelse og andre påtegninger m. m. (vedr. fast ejendom).

Bestillingsformular D

Jensen & Kjeldskov A/S, København.

Justitsministeriets genpartpapir. Til skøder, skadesløsbreve, kvitteringer til udslettelse og andre påtegninger m. m. (vedr. fast ejendom).

Mtr. nr., ejerlav, sogn: 21 b Øster Sundby
(i København kvarter) Aalborg Købstads Jorder.
eller (i de sønderjydske landsdele) **bd. og bl. i tingbogen, art. nr., ejerlav, sogn.**

Akt: Skab 8 **nr.** 122
(udfyldes af dommerkontoret)

Købers / Kreditors bopæl: **Aalborg Hypothekforening.**

Gade og hus nr.: Bakkegaardsvej 1.
(hvor sådant findes)

Anmelderens navn og bopæl (kontor):
AALBORG DISKONTOBANK A/S
VEJGAARD AFDELING

Stempel: 20 kr. 20 øre.
29. AUG. 1961 * 08709

Dette Pantebrev kan ikke overdrages til Eje eller Pant eller gøres til Genstand for individuel Retsforfølgning.

Pantebrev.

Undertegnede Kleinsmed JOHAN E. JENSEN, Aalborg,

erkender herved som Medlem af

Hypothekforeningen for Laan mod sekundær Prioritet i faste Ejendomme i Aalborg

at have modtaget et Laan i Foreningens 5 % 8. Afdeling, stort 10.100,- Kr.,

hvilke ti Tusinde eet Hundrede Kroner ----------

er udbetalt i Foreningens 5 % rentebærende Kasseobligationer af 8. Afdeling.

Af Laanets Hovedstol betales en uforanderlig **halvaarlig Ydelse**, nemlig:

a. $3^1/_4$ % af det ovennævnte Laans oprindelige Beløb. (Heraf anvendes $3^1/_{10}$ % til Laanets Forrentning og ordinære Amortisation, saaledes at $2^1/_2$ % af det til enhver Tid skyldige Beløb beregnes som Rente, det øvrige som Afdrag. Resten tilfalder Reserve- og Administrationsfondet.)

b. et ekstraordinært Afdrag, stort 0 Kr., er Nul Kroner.

Den halvaarlige Ydelse beregnes for Halvaarene 11. December til 11. Juni og 11. Juni til 11. December og forfalder til Betaling henholdsvis til hver herefter kommende 20. April og 20. Oktober, første Gang den 20. Oktober 1961, regnet for Tiden fra 11. Juni 1961 til 11. December 1961.

Som **Indskud** til Foreningens Reserve- og Administrationsfond erlægges 3 % af Laanets Beløb. Heraf betales 1 % ved Laanets Modtagelse; Resten med en Fjerdedel i hver af de 4 første efter Laanets Udbetaling kommende ovennævnte Betalingsterminer.

Til Sikkerhed for alle Betalinger efter dette Pantebrev giver Debitor herved Hypothekforeningen Panteret i den Debitor tilhørende Ejendom, beliggende Bakkegaardsvej Nr. 1 og skyldsat under Matr. Nr.: 21 b Øster Sundby, Aalborg Købstads Jorder, hvilken Ejendom tilhører mig ifølge endeligt Skøde tinglyst 18. Juni 1959.

Panteretten efter dette Pantebrev rykker op, efterhaanden som de foranstaaende Pantebreve afdrages.

Det bemærkes, at det Pantsatte, hvis Arealindhold udgør 428 m², er brandforsikret for 35.350,- Kr. ~~og vurderet til~~ ~~Kr.~~

De Pantebehæftelser, der af Foreningen respekteres som forudprioriterede for eller ligeprioriterede med dette Pantebrev er:

Kr. 9.648,44 til Aalborg Bys og Omegns Sparekasse til varierende Rente, hvilken Prioritet, der forrentes og afdrages gennem en halvaarlig Ydelse, i Tingbogen henstaar uaflyst for op. 10.000,- Kr.

Følgende Servituter og Byrder respekteres: Ingen.

Genpartens rigtighed bekræftes.
DOMMEREN I AALBORG RET. 3. AFD.

Linde

Indført i dagbogen for Aalborg rets 3. afd. den 29. AUG. 1961

AFLYST

Linde

Af Hensyn til § 18 i Lov om Ægteskabets Retsvirkninger tiltræder jeg, Fru DAGNY ANDREA JENSEN, født JENSEN, der er Pantedebitors Ægtefælle og myndig, ved min Medunderskrift foranstaaende Pantsætning.

Debitor underkaster sig følgende for alle Foreningens Medlemmer fælles Vilkaar (Justitsministeriets Pantebrev-Formular X).

.....

Aalborg, den 22. august 1961

Dagny Jensen
sign.

J. Edv. Jensen
sign.

Til Vitterlighed om Underskriftens Ægthed, Dateringens Rigtighed og Debitors og Ægtefælles Myndighed:

Navn: (sign.) H. Timsgård
Stilling: ejendomsmægler
Bopæl: Jernbanegade 3, Aalborg

Navn: (sign.) Kirsten Lind
Stilling: Fuldmægtig
Bopæl: Herluf Trollesgade 7, Aalborg

Mtr. nr., ejerlav, sogn: (i København kvarter) eller (i de sønderjydske landsdele) bd. og bl. i tingbogen, art. nr., ejerlav, sogn.

21 b, Øster Sundby, Aalborg. købstads jorder.

Gade og hus nr.:

Akt: Skab 26 nr. 122 (udfyldes af dommerkontoret)

Meddelelser i h.t.

Kreditors bopæl: rpl. § 561 og andre meddelelser, som efter loven skal tilgaa kreditor, ønskes tilsendt A/S Aalborg Diskontobank Vejgaard Afdeling.

Anmelder:

OVERRETSSAGFØRER
GEORG RENDBECK
&
LANDSRETSSAGFØRER
A. C. LAURITZEN
AALBORG

Skt. 40. ovhr.

PANTEBREV

(Ejerpantebrev)

Underskrevne Klejnsmed Johan E. Jensen, Bakkegaardsvej 1, Vejgaard pr. Aalborg,

meddeler herved mig selv eller den, til hvem dette pantebrev overdrages, panteret for et beløb af

kr.: 20.000.-,

~~med~~ uden personligt gældsansvar for mig for det anførte beløb i tilfælde af pantebrevets overdragelse til andre, være sig til ejendom eller til sikkerhed, hvilke tyve tusinde---------- kr. ---øre jeg forpligter mig til at forrente fra overdragelsens tidspunkt at regne med 6 pr. c., hvilke ----------seks---------- procent årlig erlægges i hver 11. juni og 11. december termin, første gang i den første efter overdragelsen indtrædende termin for det da forløbne tidsrum.

Dette pantebrev kan til enhver tid opsiges af kreditor eller debitor med 14 dages varsel.

Til sikkerhed for alle betalinger efter dette pantebrev giver jeg herved kreditor 3 prioritets panteret i den mig ifølge tinglyst adkomst tilhørende ejendom

matr. nr. 21 b, Øster Sundby, Aalborg købstads jorder, af hartkorn 0 alb. og af areal 439 m²

Panteretten er oprykkende efter de nedennævnte hæftelser efterhånden og for så vidt som disse afdrages eller — til et forud angivet bestemt tidspunkt — indfries.

Bestillingsformular Æ 2

Jensen & Kjeldskov A/S, København.

Foranstående ~~og xxxxxxxx~~ pantehæftelser:

kr. 10.000.- iflg. pantebrev lyst 18/4 1959 til Aalborg bys og omegns sparekasse

- 5.000.- iflg. pantebrev lyst 18/4 1959 til Aalborg bys og omegns sparekasse.

Med hensyn til de ejendommen påhvilende servitutter og andre byrder

henvises til ejendommens blad i tingbogen.

NB. Meddelelser i henhold til retsplejelovens § 561 og andre meddelelser, som efter loven skal tilgaa kreditor, ønskes tilsendt A/S Aalborg Diskontobank, Vejgaard afdeling, der iøvrigt bemyndiges til paa mine vegne at underskrive paategninger af enhver art paa nærværende ejerpantebrev, herunder kvitterings-, transport-, moderations- og relaksationspaategninger.

Iøvrigt underkaster jeg mig nedenstående trykte bestemmelser. (Justitsministeriets pantebrev-formular I.)

Aalborg den 12. juni 1959.

J. Edv. Jensen

Underskrevne bevidner herved, at ovenstående underskrift af debitor er ægte, at underskriftens dato er rigtig, og at debitor er myndig. A. C. Lauritzen, Landsretssagfører, Aalborg.

Tinglysningspåtegninger:

INDFØRT I DAGBOGEN

06656 18. JUN. 1959 Genpartens rigtighed bekræftes.
Civildommeren i Aalborg Købstad m.

AALBORG CIVILRET.

Lyst.

Linde

Linde

Mtr. nr., ejerlav, sogn: (i København kvarter) eller (i de sønderjydske landsdele) bd. og bl. i tingbogen, art. nr., ejerlav, sogn.

21 b, Øster Sundby, Aalborg købstads jorder.

Stempel: kr. øre

Akt: Skab 8 nr. 122 (udfyldes af dommerkontoret)

Gade og hus nr.:

Købers / Kreditors bopæl:

Anmelder:

AALBORG KOMMUNALE ADMINISTRATION

19.MAJ1961* 04916

Justitsministeriets genpartpapir. Til skøder, skadesløsbreve, kvitteringer til udslettelse og andre påtegninger m. m. (vedr. fast ejendom).

Påtegning

på ejerpantebrev, 20.000 kr., udstedt af klejnsmed Johan E. Jensen, tinglyst 18. juni 1959 på matr. nr. 21 b af Øster Sundby, Aalborg købstads jorder:

Efter at det foran pantsatte matr.nr. 21 b, Øster Sundby, 492 m², Aalborg købstads jorder, ved landbrugsministeriets skrivelse af 15. februar 1961 er udstykket således:

matr.nr. 21 b Øster Sundby af areal 428 m²

matr.nr. 21 mn Øster Sundby af areal 64 m²

meddeles herved samtykke til, at

matr.nr. 21 mn Øster Sundby af areal 64 m²

må udgå af pantet ifølge nærværende ejerpantebrev, som herefter alene giver pant i:

matr.nr. 21 b Øster Sundby af areal 428 m²

oprykkende næst:

opr. kr. 10.000,- til Aalborg Bys Sparekasse

" " 5.000,- " samme.

Aalborg, den 16. maj 1961.

J. Edv. Jensen.

Indført i dagbogen for Aalborg rets 3. afd.

den 19.MAJ.1961

LYST

Linde

Genpartens rigtighed bekræftes.

DOMMEREN I AALBORG RET. 3. AFD.

Linde

Bestillingsformular D

Jensen & Kjeldskov A/S, København

Mtr. nr., ejerlav, sogn: (i København kvarter) eller (i de sønderjydske landsdele) bd. og bl. i tingbogen, art. nr., ejerlav, sogn.

21-b Øster Sundby, Aalborg købstads jorder

Stempel: kr. øre

Akt: Skab 8 nr. 122 (udfyldes af dommerkontoret)

Købers / Kreditors bopæl: Aalborg

Gade og hus nr.: Bakkegaardsvej 1

Anmelder:

AALBORG DISKONTOBANK A/S
Vejgaard afdeling

29. AUG. 1961* 08710

Justitsministeriets genpartpapir. Til skøder skadesløsbreve, kvitteringer til udslettelse og andre påtegninger m. m. (vedr. fast ejendom).

P a a t e g n i n g

paa ejerpantebrev kr. 20.000,- udstedt d. 12/6 1959 af kleinsmed Johan Edv. Jensen, Aalborg, lyst den 18/6-1959 og senere.

Nærværende ejerpantebrev skal fremtidig respektere:

opr. kr. 10.000,- til Aalborg Bys Sparekasse
" " 10.100,- " Aalborg Hypothekforening 5% 8. afd.

Aalborg, den 29. august 1961.

J. Edv. Jensen
sign.

Indført i dagbogen for Aalborg rets 3. afd.
den 29. AUG. 1961

LYST

Linde

Genpartens rigtighed bekræftes.
DOMMEREN I AALBORG RET. 3. AFD.

Linde

Bestillingsformular D

Jensen & Kjeldskov A/S, København.

Mtr. nr., ejerlav, sogn: 21-b Stempel: kr. øre Akt: Skab E nr. 122
(udfyldes af dommerkontoret)
(i København kvarter) Østersundby
eller (i de sønderjydske landsdele) bd. og bl. i tingbogen, art. nr., ejerlav, sogn.

Købers / Kreditors } bopæl:

Gade og hus nr.: Bakkegaardsvej 1

Anmelder:

AALBORG DISKONTOBANK A/S
VEJGAARD AFDELING

24. NOV. 1961* 12087

Justitsministeriets genpørtpapir. Til skøder skadesløsbrove, kvitteringer til udslettelse og andre påtegninger m. m. (vedr. fast ejendom).

P A A T E G N I N G

paa ejerpantebrev stort kr. 20.000,- udstedt 12/6 1959 af kleinsmed J. Edv. Jensen, Bakkegaardsvej 1, Aalborg, lyst 18/6 1959 og senere:

Nærværende ejerpantebrev stort kr. 20.000,- transporterer og endeligt overdrager jeg J. Edv. Jensen til chauffør John Ringgren, Bakkegaardsvej 1, Aalborg, der nu er ejer af den pantsatte ejendom og med alle til pantebrevet knyttede rettigheder. For overdragelsen er jeg fyldestgjort.

Iøvrigt rathihaberes ejerpantebrevet i alle dets ord og punkter.

Aalborg, den 21. november 1961.

John Ringgren
sign.

J. Edv. Jensen
sign.

Til vitterlighed om underskrifternes ægthed, dateringens rigtighed og underskrivernes myndighed:

A. Nøhr (sign.)
Bankbestyrer
Aalborg

A. Bork (sign.)
Bankassistent
Aalborg

Bestillingsformular D

Jensen & Kjeldskov A/S, København.

Indført i dagbogen for
Aalborg rets 3. afd.

den 24. NOV. 1961

LYST

Linde

Genpartens rigtighed bekræftes.
DOMMEREN I AALBORG RET. 3. AFD.
Linde

Mtr. nr., ejerlav, sogn: (i København kvarter) eller (i de sønderjydske landsdele) bd. og bl. i tingbogen, art. nr., ejerlav, sogn.

21a m.fl. Øster-Sundby under Aalborg Købstads Jorder.

Stempel: kr. øre

Akt: Skab 6 nr. 122 (udfyldes af dommerkontoret)

(HÆK)

Justitsministeriets genpartpapir. Til lejekontrakter, serviceudokumenter o.l., fortsættelse af dokumenter, fortegnelse pantsatte genstande o.l. (vedr. fast ejendom).

Gade og hus nr.:

Anmelder:

Landinspektørfirmaet Nellemann, Vesteraa 1, Aalborg.

Stempelfri i henhold til lov nr. 199 af 31. maj 1963 om hovedlandeveje, § 14.

24. SEP. 1970 * 15376

Deklaration

I medfør af § 41 i vejbestyrelsesloven (lovbekendtgørelse nr. 342 af 9. december 1964) har Ministeren for offentlige Arbejder pålagt byggelinier på de på vedhæftede plan, udfærdiget i juni 1967 af landinspektør Poul Brassøe, angivne arealer langs de i lov nr. 386 af 4. december 1963 omhandlede motorvejsanlæg, der skal udføres i tilslutning til en tunnelforbindelse under Limfjorden.

Fremtidig bebyggelse, hvad enten bebyggelsen sker på en hidtil ubebygget del af en grund, ved ombygning af en bestående bygning eller i stedet for nedbrændte eller nedrevne bygninger skal holdes bag byggelinierne. Hvad der i henhold til foranstående gælder om bygninger, gælder også om sportspladser, kirkegårde, tankanlæg og andre anlæg af blivende art.

Byggelinierne pålægges i en mindsteafstand fra planumskant (normalt lig vejskel, hvor vejen ligger i terrænhøjde) som angivet på ovennævnte plan, idet det bemærkes, at anvendelsen af den angivne mindsteafstand forudsætter, at bygningen opføres med sin jordlinie i fremtidig vejhøjde. Er dette ikke tilfældet, skal bygningen rykke så meget længere tilbage, som normalt svarer til 2 gange højdeforskellen, foruden den fornødne bredde til passage foran bygningen mindst 1 m.

Nærmere oplysninger om byggelinierne vil kunne indhentes hos stadsingeniøren i Aalborg.

vend!

Bestillingsformular G

Jensen & Kjeldskov A/S, København

Foranstående begæres, i medfør af ovennævnte lovs § 44 med prioritet forud for pantegæld og andre rettigheder over ejendommen, uanset hvornår sådanne rettigheder over ejendommene er erhvervet, tinglyst servitutstiftende for så vidt angår følgende ejendomme, der berøres af byggeliniepålægget:

Matr.nr. 21^{a}, 21^{b}, 21^{g}, 21^{h}, 21^{i}, 21^{mn}, 21^{nz} og 44 Øster-Sundby under Aalborg Købstads Jorder.

Påtaleberettiget er Ministeriet for offentlige Arbejder.

Pålagt for Ministeriet for offentlige Arbejder af Aalborg Byråd.

Ifølge Aalborg Byråds bemyndigelse

Aalborg, den 3. august 1970

Hans Brusgaard / Viktor Saaby (sign.)
rådmand sekretariatschef

Indført i dagbogen for
Aalborg rets 3. afd.

den 24. SEP. 1970

LYST

Linde

Genpartens rigtighed bekræftes.
DOMMEREN I AALBORG RET 3. AFD.

Linde

AV 6159
20.100 5

Signaturforklaring:
- - - - : Byggelinie
(HÅK)

Akt: Skab nr.
(udfyldes af dommerkontoret)

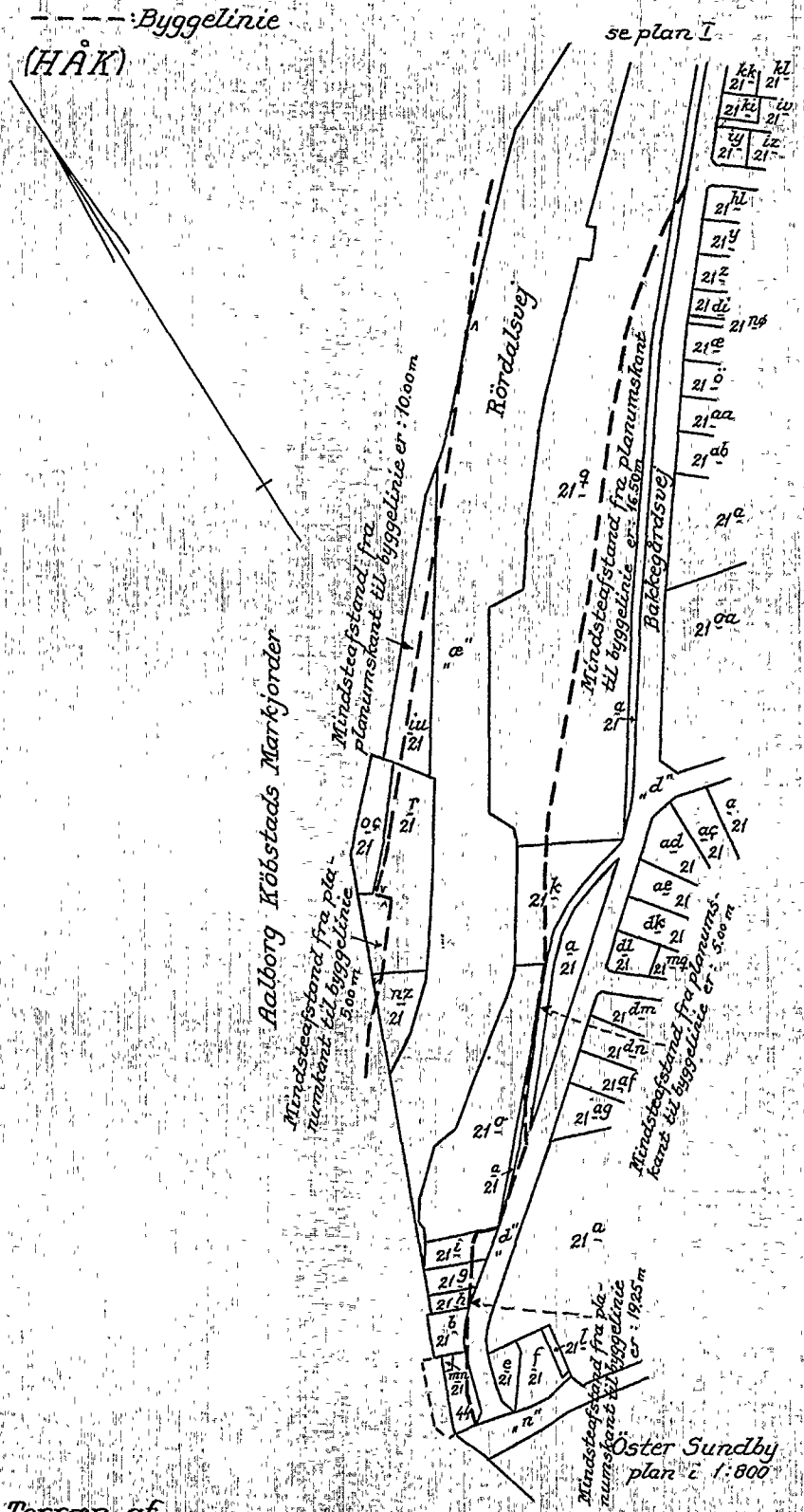

Terræn af

Öster Sundby - Plan II

under Aalborg Köbstads Jorder

Nærværende kort er d.d. a-jour-ført.

Aalborg, den 20. august 1970

Landinspektør

Udfærdiget til brug ved tinglysning af byggelinier i forbindelse med motorvejsanlæg i tilslutning til limfjordstunnel

Aalborg i juni 1967

Nic. Nellemann - Ib Nellemann - Axel Pedersen

Paul Brasse
Landinspektør

1:4000

At denne kort-genpart er nøjagtig genpart af det originale kort vedrørende ejendommen(e)
● Öster- ● Sundby under Aalborg ● Köbstads ● Jorder
mtr. nr. 21a 21b 21g 21h 21i 21mn 21nz 21-44
Aalborg d. 1. juni 1967 Navn: Paul Brasse
attesteres herved.

Justitsministeriets genpartkalkulerred. Til kort.

Bestillingsformular
Y-1 fløj
Jensen & Kjeldskov A/S
GB

Akt: Skab E nr. 122
(udfyldes af dommerkontoret)

Anmelder: Aalborg Kommune, Teknisk Forvaltning, Vesterbro 14, 9000 Aalborg. Tlf. 9931 3131

Justitsministeriets genpartpapir.

Planbestemmelser
Lokalplan 11-011

Boligområde, Bakkegårdsvej 1, Vejgård

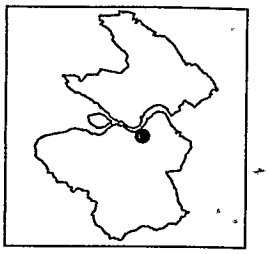

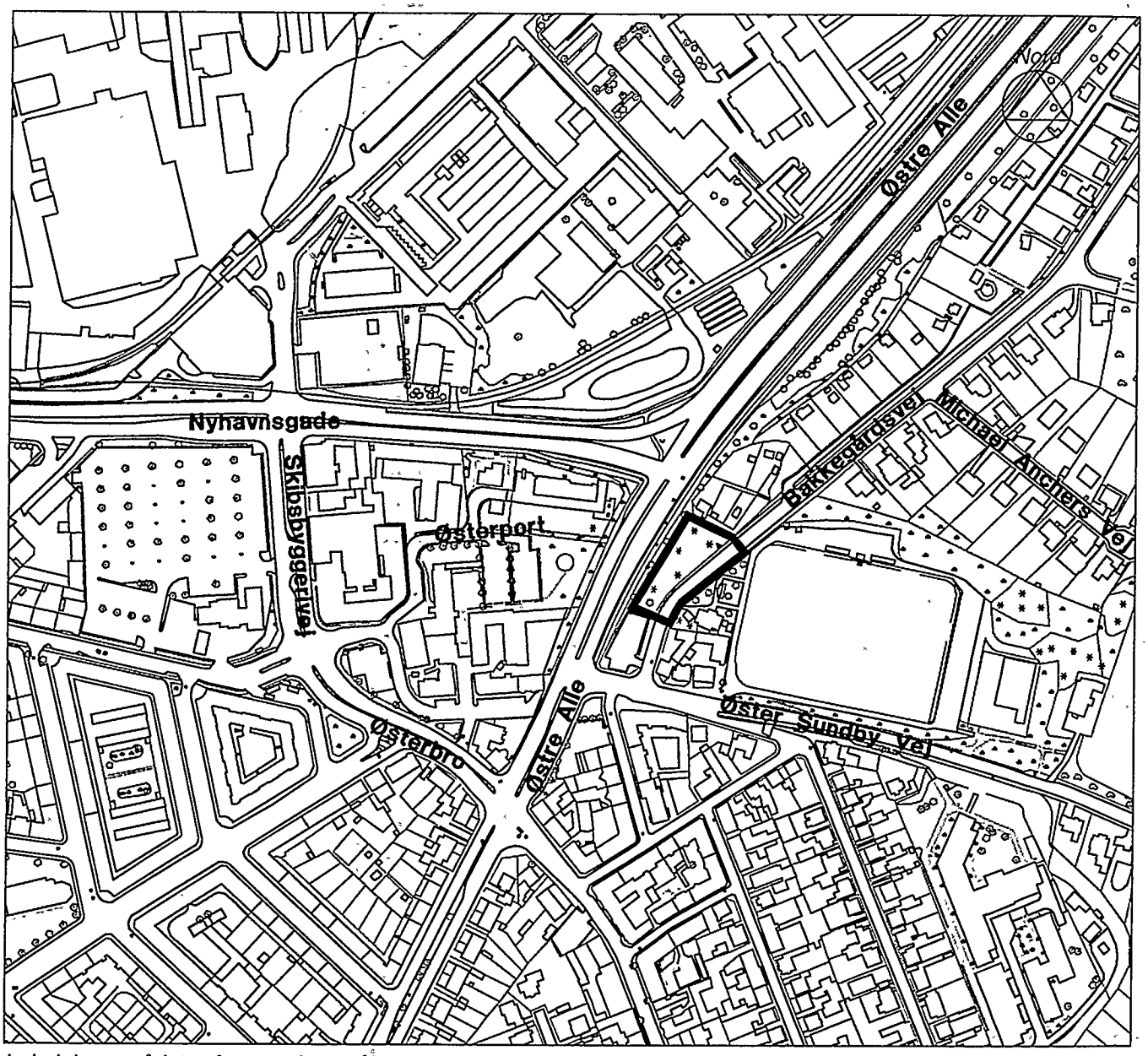

Lokalplanområdets afgrænsning, mål 1:4000.

Indledning

Lokalplanens bestemmelser er bindende og tinglyses på de ejendomme, der omfattes af lokalplanen. Tekst i *kursiv* har til formål at forklare og illustrere lokalplanbestemmelserne. Tekst skrevet i *kursiv* er altså ikke lokalplanbestemmelser og er således ikke bindende.

Den danske Landinspektørforenings Forlagsvirksomhed Blanketnummer 278 A

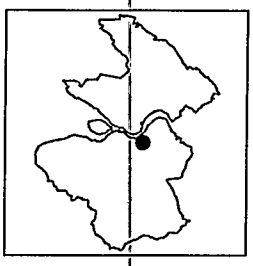

Planbestemmelser
Lokalplan 11-011

Boligområde, Bakkegårdsvej 1, Vejgård

1. Formål

Lokalplanens formål er at sikre:

at området kan anvendes til boligformål i form af tæt-lav bebyggelse med tilhørende fællesanlæg,

at ny bebyggelse placeres inden for et fastlagt byggeområde,

at bebyggelsesprocenten ikke overstiger 25, og

at der fastholdes træbeplantningsbælter mellem bebyggelsen og henholdsvis Bakkegårdsvej mod øst og Østre Allé mod vest.

2. Område og zonestatus

2.1 Matrikeloversigt
Lokalplanens område er vist på Bilag 1 og 2.

Lokalplanen omfatter følgende matrikelnummer:

Øster Sundby, Aalborg Jorder
21 b, del af offentligt vejareal "d "(Bakkegårdsvej) samt alle parceller, der efter den 1. september 2001 udstykkes fra den nævnte ejendom inden for lokalplanens område.

2.2 Zoneforhold
Lokalplanområdet er i landzone. Med bekendtgørelsen af den endeligt vedtagne lokalplan vil hele området blive overført til byzone.

Der overføres følgende arealer til byzone:
Matr. nr. 21 b, Øster Sundby, Aalborg Jorder: 1298 m².

Del af off. vejareal "d": ca. 800 m².



Bakkegårdsvej / Øster Sundby Vej med lokalplanområdets træbeplantning i baggrunden.

Justitsministeriets genpartpapir.

Planbestemmelser
Lokalplan 11-011

Boligområde, Bakkegårdsvej 1, Vejgård

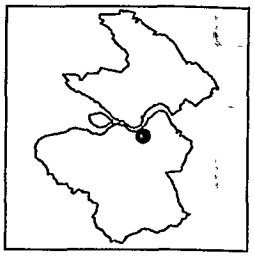

3. Arealanvendelse

3.1 Anvendelse

* Boliger (åben-lav, tæt-lav)
* Rekreative formål
* Tekniske anlæg

Inden for området kan der indrettes lokaler eller opføres bebyggelse til fælles brug for beboere og ansatte (fælleshuse, redskabsskure, cykelskure m. m.).

4. Udstykning

4.1 Grundstørrelse

En grund til en enkelt, selvstændig bolig i tæt-lav boligbebyggelse må ikke udstykkes med en størrelse, der er mindre end 65 m^2.

5. Bebyggelsens placering og omfang

5.1 Byggelinier

Bebyggelse må ikke opføres nærmere skel mod naboejendomme og vej end de byggelinier, der er vist på Bilag 2.

5.2 Bebyggelsesprocent

Bebyggelsesprocenten må ikke overstige 25.

5.3 Etageantal og bygningshøjde

Bebyggelse må opføres med højst én etage med udnyttelig tagetage. Bygninger må ikke være højere end 8,5 m over terrænniveau eller over niveauplaner, der er fastsat for den pågældende grund.

6. Bebyggelsens udseende

6.1 Ydervægge

Ydervægge skal fremtræde med træbeklædte facader og gavle, som blank murværk i tegl eller som murværk, der er vandskuret.

6.2 Tagbeklædning

Tagbeklædning kan udføres af tagsten af tegl eller beton, af eternitskifer eller af tagpap.

7. Ubebyggede arealer

7.1 Træbeplantning

Der skal fastholdes træbeplantning i et 5 m bredt bælte langs vejskel mod Bakkegårdsvej og mod Østre Allé.

Beplantning skal i overvejende grad bestå af løvfældende træer og buske.

7.2 Terrænregulering m. m.

Terrænreguleringer på mere end +/- 0,5 m i forhold til eksisterende terræn (færdigreguleret terræn efter byggeriets fuldførelse), eller terrænreguleringer nærmere skel end 1,0 m må ikke foretages uden Aalborg Kommunes tilladelse.

8. Veje, stier og parkering

8.1 Vejadgang

Vejadgang til lokalplanens område må kun ske fra Bakkegårdsvej som vist i princippet på Bilag 2.

8.2 Parkering

Der udlægges areal til parkering i overensstemmelse med Aalborg Kommunes vejledende parkeringsnormer. Se Bilag F.

9. Tekniske anlæg

9.1 Ledninger i jord

Ledninger for el, telefon, antenne og lignende må kun udføres som jordkabler.

9.2 Antenneanlæg

Der må ikke opsættes udendørs antenneanlæg, der synlige fra offentlige veje, stier, pladser m. m.

Den danske Landinspektørforenings Forlagsvirksomhed Blanketnummer 278A

10. Miljø

10.1 Miljøklassificering

Inden for lokalplanens område må der kun etableres virksomhed inden for miljøklasse 1 - 2. Se Bilag A.

10.2 Trafikstøj

Ny boligbebyggelse skal beskyttes mod trafikstøjgener fra Østre Allé. For at opnå et acceptabelt støjniveau i bebyggelsen skal det tilstræbes, at det indendørs støjniveau fra vejtrafik ikke overstiger 30 dB(A) i beboelsesrum.

Udendørs opholdsarealer skal primært placeres, så støjniveauet fra vejtrafikken så vidt muligt ikke overstige 65 dB(A).

Trafikstøj skal måles som anført i Miljøstyrelsens vejledning om trafikstøj i boligområder.

11. Grundejerforening

Ingen bestemmelser.

12. Betingelser for at ny bebyggelse må tages i brug

12.1 Fjernvarmepligt

Ny bebyggelse eller ændret anvendelse må ikke uden Aalborg Kommunes tilladelse tages i brug før den er tilsluttet et kollektivt varmeforsyningsanlæg efter kommunens anvisning.

Forholdet til deklaration om byggelinie langs Østre Allé

Gennemførelse af bebyggelse inden for den største del af lokalplanens byggefelt forudsætter, at der inden for lokalplanområdet dispenseres fra den vejbyggelinie, der er fastlagt langs Østre Allé, og som er tinglyst servitutstiftende på bl.a. matr. nr. 21 b, Øster Sundby, Aalborg Jorder den 24.09.1970.

Aalborg Kommune, Teknisk Forvaltning har som vejmyndighed meddelt en sådan dispensation den 25. april 2001 på vilkår, at bygninger med anlæg pålægges deklaration om fjernelse i påkommende tilfælde uden udgift for Aalborg Kommune som vejmyndighed.

Akt: Skab nr.
(udfyldes af dommerkontoret)

Justitsministeriets genpartpapir.

Planbestemmelser
Lokalplan 11-011

Boligområde, Bakkegårdsvej 1, Vejgård

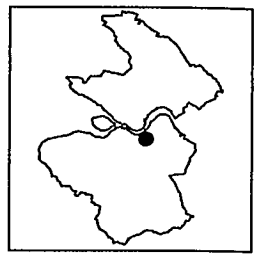

Retsvirkninger

Når den endeligt vedtagne lokalplan er offentligt bekendtgjort må der hverken retligt eller faktisk etableres forhold i strid med planens bestemmelser, medmindre der gives dispensation.

Det betyder bl.a. at den hidtidige lovlige brug af ejendommene kan fortsætte, hvorimod fx ændret brug, bebyggelse eller udstykning ikke må stride mod lokalplanen.

Byrådet kan dispensere fra lokalplanen, hvis det ikke strider mod planens principper. Mere væsentlige afvigelser kræver derimod udarbejdelse af en ny lokalplan.

Lokalplanen fortrænger private tilstandsservitutter, der strider mod planen.

Når det er nødvendigt for at virkeliggøre lokalplanen kan byrådet ekspropriere.

GENPART 032453 03 0001.2176 27.02.2002 TA
900,00 K

Vedtagelse

Lokalplan 11-011er endeligt vedtaget af Aalborg Byråd den 14/1 2002

Henning G. Jensen
borgmester

Jens Kristian Munk
kommunaldirektør

Lokalplanen er offentligt bekendtgjort den 19-01-2002
fra hvilken dato planen har retsvirkning.

Thina Wallin
planlægger

Den danske Landinspektørforenings Forlagsvirksomhed Blanketnummer 278A

Akt: Skab nr.
(udfyldes af dommerkontoret)

Justitsministeriets genpartpapir.

Erhvervskategorier: Bilag A
Lokalplan 11-011

Boligområde, Bakkegårdsvej 1, Vejgård

Vejledning om miljøklasser og beskyttelsesafstande

Virksomhederne er opdelt i 7 miljøklasser, hvor klasse 1 er den mindst miljøbelastende, og klasse 7 den mest miljøbelastende.

Klasse 1 omfatter virksomheder og anlæg, som *kun påvirker omgivelserne i ubetydelig grad*, og således kan integreres med boliger.

Klasse 2 omfatter virksomheder og anlæg, som *kun påvirker omgivelserne i ringe grad*, og ville kunne indplaceres i områder, hvor der også findes boliger.

Klasse 3 omfatter virksomheder og anlæg, som *kun påvirker omgivelserne i mindre grad*, og som bør placeres i erhvervs- eller industriområder evt. i randzonen tættest ved forureningsfølsom anvendelse.

Klasse 4 omfatter virksomheder og anlæg, som *er noget belastende for omgivelserne*, og derfor som hovedregel bør placeres i industriområder.

Klasse 5 omfatter virksomheder og anlæg, som *er ret belastende for omgivelserne*, og derfor skal placeres i industriområder.

Klasse 6 omfatter virksomheder og anlæg, som *er meget belastende for omgivelserne*, og derfor skal placeres i større industriområder, så den ønskede afstand i forhold til forureningsfølsomme naboer kan opnås.

Klasse 7 omfatter virksomheder og anlæg, som *er særligt belastende for omgivelserne*, og derfor som hovedregel skal placeres i områder, indrettet til særligt miljøbelastende virksomhed (normalt kommuneplanens M-områder).

Herudover findes der en række virksomheder og anlægstyper med specielle beliggenhedskrav, hvor afstanden til boligområder skal være større end 500 meter. Som eksempel kan nævnes særligt risikobetonet produktion, større skibsværfter, flyvepladser, skydebaner, motorsportsbaner og lignende.

Der opereres med følgende minimumsafstandskrav:

Klasse 1	0 meter	(i forhold til boliger)
Klasse 2	20 meter	(i forhold til boliger)
Klasse 3	50 meter	(i forhold til boliger)
Klasse 4	100 meter	(i forhold til boliger)
Klasse 5	150 meter	(i forhold til boliger)
Klasse 6	300 meter	(i forhold til boliger)
Klasse 7	500 meter	(i forhold til boliger)

Der kan forekomme situationer, der berettiger virksomheder til en anden miljøklassificering, end angivet i skemaet "Erhvervskategorier" på de følgende sider. Fx hvis en virksomhed foretager forureningsbegrænsende foranstaltninger udover det, der er normalt i forhold til gængse forureningsbegrænsende produktionsmetoder. I så fald kan en lavere klassificering accepteres, d.v.s. en kortere nødvendig afstand i forhold til forureningsfølsomme formål som f.eks. boliger. Omvendt kan det være nødvendigt at klassificere en virksomhed højere end forudsat, hvis virksomheden forurener udover, hvad der er normalt for den pågældende virksomhedstype.

Der er altså **ikke** tale om afstandskrav, der **skal** overholdes. Men hvis afstanden tillades kortere end den, der fremgår af skemaet på de følgende sider, må det ske ud fra en konkret vurdering af den enkelte virksomheds forureningsbelastning på både kort og langt sigt.

Den danske Landinspektørforenings Forlagsvirksomhed Blanketnummer 278 A

Bilag A: Erhvervskategorier
Lokalplan 11-011

Boligområde, Bakkegårdsvej 1, Vejgård

Anvendelse	Eksempler på virksomhedstyper	Miljøklasse	Bemærkninger
Rekreative formål	Grønne områder Parker Torve, pladser o.l.		
Tekniske anlæg	Antenneanlæg (små) P-pladser Pumpestation o.l. Transformere (små)	 1-3 1-4 	 Det forudsættes, at anlæggene kan indpasses på en harmonisk måde.

Justitsministeriets genpartpapir

Støj fra erhverv: Bilag B
Lokalplan 11-011

Boligområde, Bakkegårdsvej 1, Vejgård

Vejledende grænseværdier for støjbelastning - målt udendørs - fra den enkelte virksomhed, anlæg eller indretning. Der er grænseværdier ***både*** for det område, hvori virksomheden, anlægget eller indretningen ligger ***og*** for omliggende områder.

Arealanvendelse	**Det ækvivalente, korrigerede støjniveau i dB(A)**		
	Mandag - fredag 07.00 - 18.00 Lørdag 07.00 - 14.00	Mandag - fredag 18.00 - 22.00 Lørdag 14.00 - 22.00 Søn- og helligdage 07.00 - 22.00	Alle dage 22.00 - 07.00 (Maksimalværdier om natten er anført i parantes)
Erhvervsområder for særlige virksomheder (M-områder) Erhvervsområder for industri m.m. (I-områder), men ***kun*** i de tilfælde, hvor rammebestemmelserne åbner mulighed for støjniveau på 70 dB(A)	70	70	70
Erhvervsområder for industri m.m. (I-områder)	60	60	60
Erhvervsområder for let industri m.m. (H-områder)	60	60	60
Områder for boliger og erhverv (D-områder)	55	45	40 (55)
Centerområder (C-områder)	55	45	40 (55)
Etageboligområder og institutionsområder	50	45	40 (55)
Boligområder for åben og lav boligbebyggelse og særlig støjfølsomme institutioner (hospitaler, plejehjem m.v.)	45	40	35 (50)

Der henvises til den til enhver tid gældende vejledning fra Miljøstyrelsen om Ekstern støj fra virksomheder.

Den danske Landinspektørforenings Forlagsvirksomhed Blanketnummer 278A

Støj fra trafik: Bilag C
Lokalplan 11-011

Boligområde, Bakkegårdsvej 1, Vejgård



Støj fra vejtrafik

Støjen fra vejtrafik afhænger af antallet af biler, disses hastighed og andelen af tunge køretøjer. Ved registrering af vejtrafikstøj anvendes en gennemsnitsværdi af støjens variation i et døgn.

Under normale omstændigheder skal årsdøgntrafikken være på mellem 1.000 og 1.500 biler, før støjniveauet overstiger de 55 dB(A), der er grænsen for støjfølsomme formål, fx boliger.

Eksisterende og planlagte veje

Arealer langs eksisterende og planlagte veje må *ikke* anvendes til støjfølsomme formål, hvor trafikstøjen overstiger de grænseværdier, der er angivet i **Skema 1.**

Nye veje og varige trafikomlægninger

Ved anlæg af nye veje og ved varige trafikomlægninger, som giver øget trafik på eksisterende veje, skal følgende støjniveauer søges overholdt på arealer udlagt til støjfølsomme formål:

Nuværende udendørs vejtrafikstøjniveau:	Fremtidigt udendørs vejtrafikstøjniveau:
under 55 dB(A)	max. 55 dB(A)
55 - 65 dB(A)	max. 65 dB(A)
over 65 dB(A)	max. nuværende niveau

Anvendelse	Udendørs støjniveau	Indendørs støjniveau
Rekreative områder i det åbne land:		
- sommerhusområder	50 dB(A)	30 dB(A)
- grønne områder og campingpladser	50 dB(A)	
Rekreative områder i/nær byområder:		
- bydelsparker, kolonihaver, nyttehaver og turistcamping-pladser	55 dB(A)	
Boligområder:		
- boligbebyggelse	55 dB(A)	30 dB(A)
- daginstitutioner mv.	55 dB(A)	35 dB(A)
- opholdsarealer	55 dB(A)	
Offentlige formål		
- hospitaler	55 dB(A)	30 dB(A)
- uddannelsesinstitutioner mv.	55 dB(A)	35 dB(A)
Liberale erhverv mv.		
- hoteller	60 dB(A)	30 dB(A)
- kontorer mv.	60 dB(A)	35 dB(A)

***Skema 1:** Grænseværdier for vejtrafikstøj.*

Særlige regler for midtbyen

For at fastholde midtbyens blandede bymæssige anvendelse kan der indpasses støjfølsomme anvendelser på arealer med støjniveauer som angivet i **Skema 2**, såfremt

- det ikke er muligt at anvende arealerne til ikke støjfølsomme formål,
- antallet af støjramte boliger søges minimeret,
- mindst en facade er belastet med mindre end 55 dB(A) og sove- og opholdsrum orienteres mod denne facade,
- de primære opholdsarealer maksimalt belastes med 55 dB(A).

Anvendelse	Udendørs støjniveau	Indendørs støjniveau
Rekreative områder i/nær byområder:		
- nyttehaver og turistcamping-pladser	65 dB(A)	
Boligområder:		
- boligbebyggelse	65 dB(A)	30 dB(A)
- daginstitutioner mv.	65 dB(A)	35 dB(A)
Liberale erhverv mv.		
- hoteller	70 dB(A)	30 dB(A)
- kontorer mv.	70 dB(A)	35 dB(A)

***Skema 2:** Grænseværdier for vejtrafikstøj i midtbyen.*

Justitsministeriets genpartpapir.

Akt: Skab nr.
(udfyldes af dommerkontoret)

Parkeringsnormer: Bilag F
Lokalplan 11-011

Boligområde, Bakkegårdsvej 1, Vejgård

P

På den enkelte ejendom skal der udlægges tilstrækkeligt parkeringsareal til brug for ejenommens anvendelse efter følgende vejledende P-normer:

BEBYGGELSENS ART	P-NORMER: • Vestbyen • Aalborg midtby • Ø-gadekvarteret • Nørresundby midtby	P-NORMER: • Den øvrige del af kommunen
Boligbyggeri:		
Boliger	½ P-plads pr. bolig	
Fritliggende enfamiliehuse		2 P-pladser pr. hus
Rækkehuse, dobbelthuse og lign.		1½ P-plads pr. hus/lejlighed. P-pladser kan etableres i fælles P-anlæg
Etagehuse		1½ P-plads pr. bolig
Ungdomsboliger, kollegier, enkeltværelser	1 P-plads pr. 4 boligenheder	1 P-plads pr. 4 boligenheder
Plejehjem, ældreboliger m.v.	Såfremt indretning og benyttelse kan sidestilles med almindelige boliger, er det de almindelige krav til boliger, der er gældende. I andre tilfælde beregnes 1 P-plads for hver fjerde bolig samt de nødvendige pladser til personale og gæster.	
Erhvervsbyggeri:		
Kontor-, fabriks- og værkstedsbygninger	1 P-plads pr. 100 m²	1 P-plads pr. 50 m² etageareal (excl. garageareal)
Lagerbygninger	1 P-plads pr. 100 m²	1 P-plads pr. 100 m²
Servicestationer	10 P-pladser	10 P-pladser
Hoteller	1 P-plads pr. 4 værelser	1 P-plads pr. 2 værelser
Restaurationer og lignende	1 P-plads pr. 20 siddepladser	1 P-plads pr. 10 siddepladser
Supermarkeder/discountbutikker/større udvalgsvarebutikker	1 P-plads pr. 25 m² salgsareal samt 1 P-plads pr. 50 m² bruttoetageareal iøvrigt	1 P-plads pr. 25 m² salgsareal samt 1 P-plads pr. 50m² bruttoetageareal iøvrigt
Øvrige butikker	1 P-plads pr. 100 m²	1 P-plads pr. 50 m²
Andre erhvervsejendomme:	Fastsættes efter byrådets individuelle vurdering af antal ansatte samt kunder.	
Blandet bolig og erhverv:	Fastsættes som summen af kravet til de enkelte funktioner.	
Andet byggeri:		
Teatre, biografer og lign.	1 P-plads pr. 8 siddepladser	1 P-plads pr. 8 siddepladser
Idrætshaller	1 P-plads pr. 10 personer som hallen må rumme	1 P-plads pr. 10 personer som hallen må rumme (dog mindst 20 pladser)
Sportsanlæg	1 P-plads pr. 5 siddepladser	1 P-plads pr. 5 siddepladser
Sygehuse	1 P-.plads pr. 125 m² etageareal	1 P-plads pr. 125 m² etageareal
Skoler	1 P-plads pr. 2 ansatte samt 1 P-plads pr. 8 elever over 18 år	1 P-plads pr. 2 ansatte samt 1 P-plads pr. 4 elever over 18 år
Daginstitutioner	2 P-pladser pr. 20 normerede pladser	4 P-pladser pr. 20 normerede pladser
Såfremt en type byggeri, der ikke er nævnt i listen, ønskes opført, fastsætter byrådet i hvert enkelt tilfælde kravet til antal parkeringspladser under hensyntagen til den konkrete anvendelse.		

Den danske Landinspektørforenings Forlagsvirksomhed Blanketnummer 278A

Justitsministeriets genpartipapir.

Akt: Skab nr.
(udfyldes af dommerkontoret)

Matrikelkort: Bilag 1
Lokalplan 11-011

Boligområde, Bakkegårdsvej 1, Vejgård

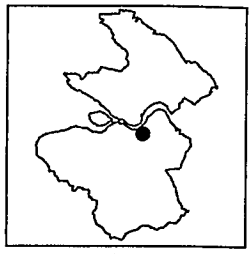

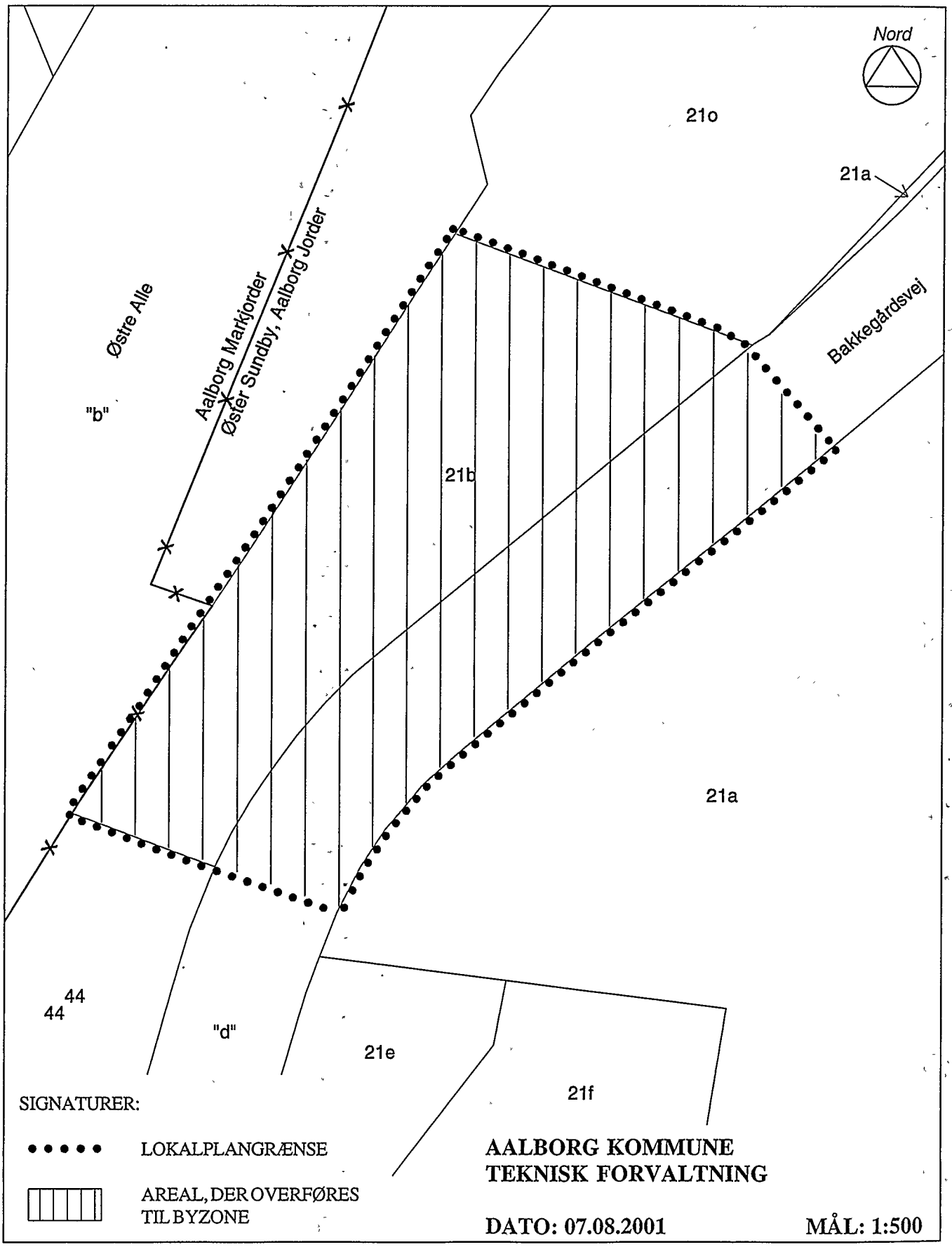

SIGNATURER:

●●●●● LOKALPLANGRÆNSE

AREAL, DER OVERFØRES TIL BYZONE

AALBORG KOMMUNE
TEKNISK FORVALTNING

DATO: 07.08.2001 **MÅL: 1:500**

Akt: Skab nr.
(udfyldes af dommerkontoret)

Justitsministeriets genpartpapir.

Arealanvendelse: Bilag 2
Lokalplan 11-011

Boligområde, Bakkegårdsvej 1, Vejgård

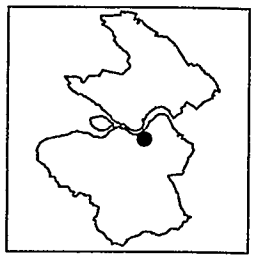

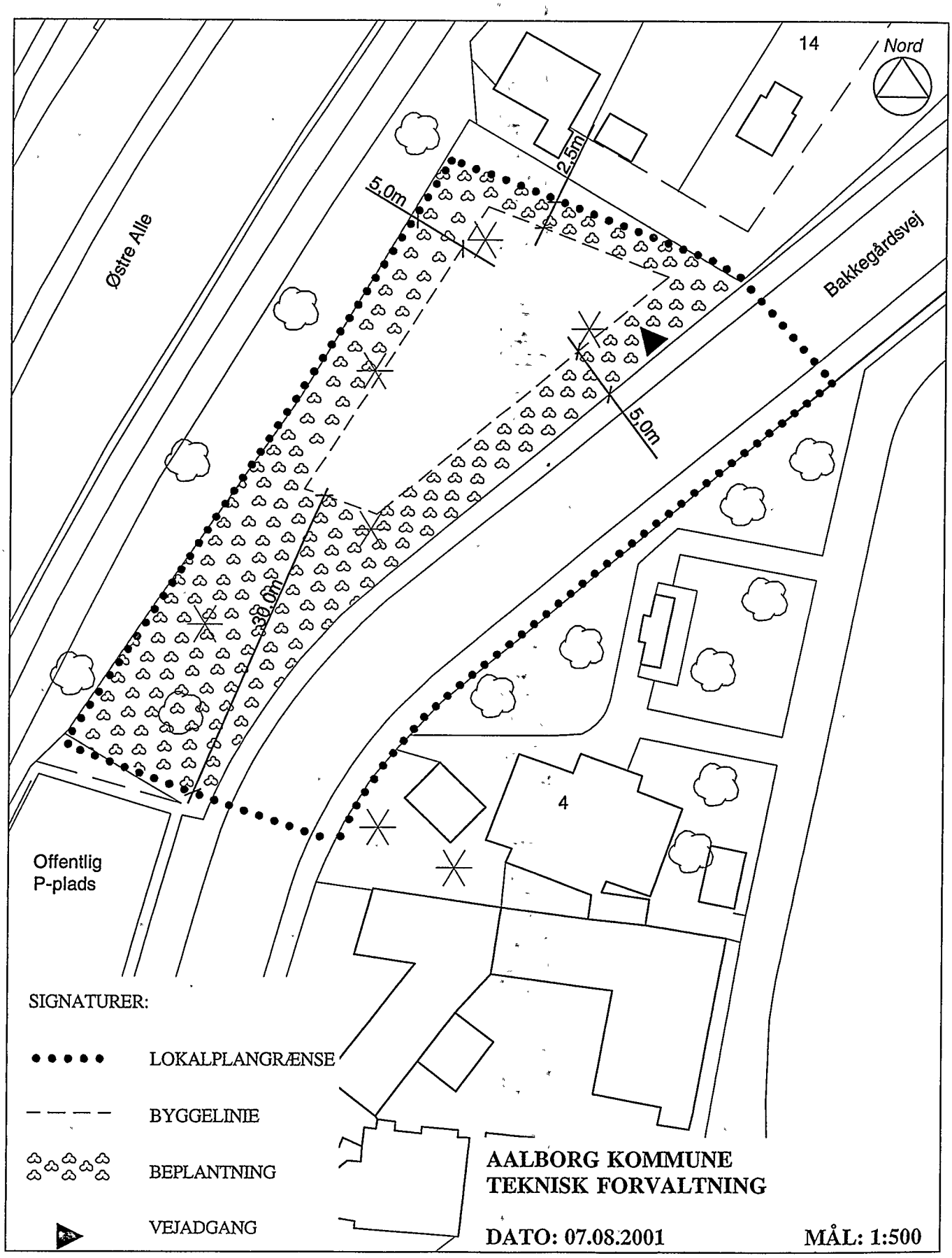

Justitsministeriets genpartpapir

*** * ***
* * *
* * ***
* * * Retten i Aalborg
* *** *** Tinglysningsafdelingen

Akt.nr.:
E 122

Påtegning på byrde
Vedrørende matr.nr. 21 B, Ø. Sundby, Aalborg Jorder
Ejendomsejer: Aalborg Kommune
Lyst første gang den: 04.02.2002 under nr. 12538
Senest ændret den : 04.02.2002 under nr. 12538

Afvist fra tingbogen f.s.v. del af offentligt vejareal "d", der ikke eksisterer i tingbogen.

Retten i Aalborg den 20.02.2002

Bitten Andersen

Otto B. Wroblewski, Nytorv 19, 1450 København K